Yachay Tech — Analisis Multi-criterio con Priorizacion de Edificaciones

Sitios requeridos + cobertura de zonas (Jardin Botanico e Innopolis) | Solar 30% · Sombra 20% · Edificacion 35% · Proximidad 15%

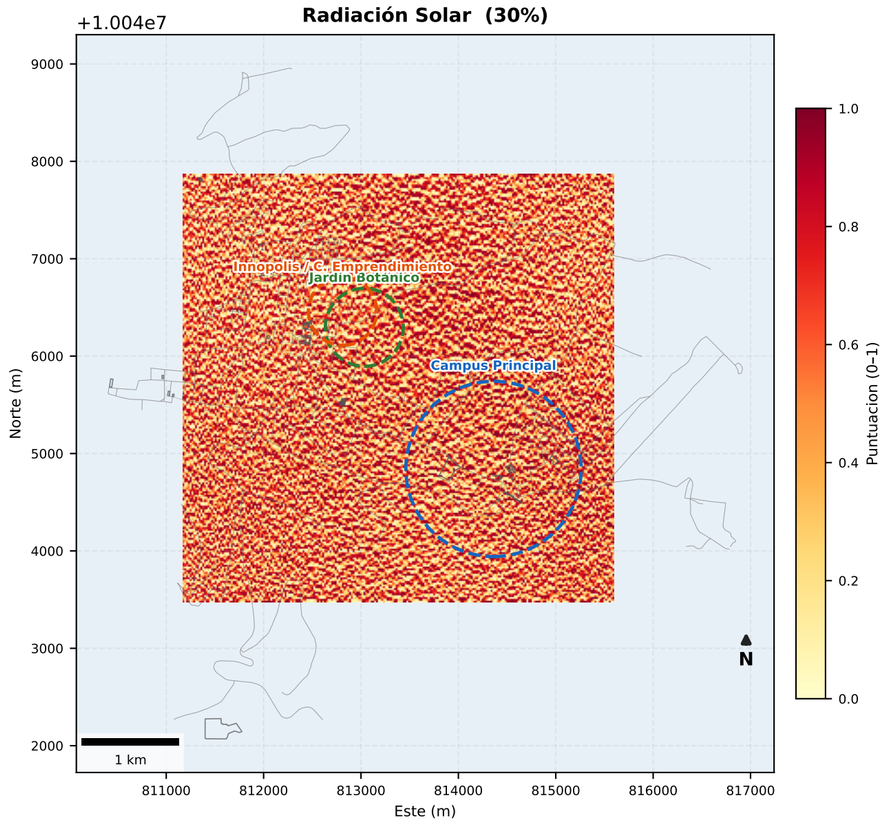

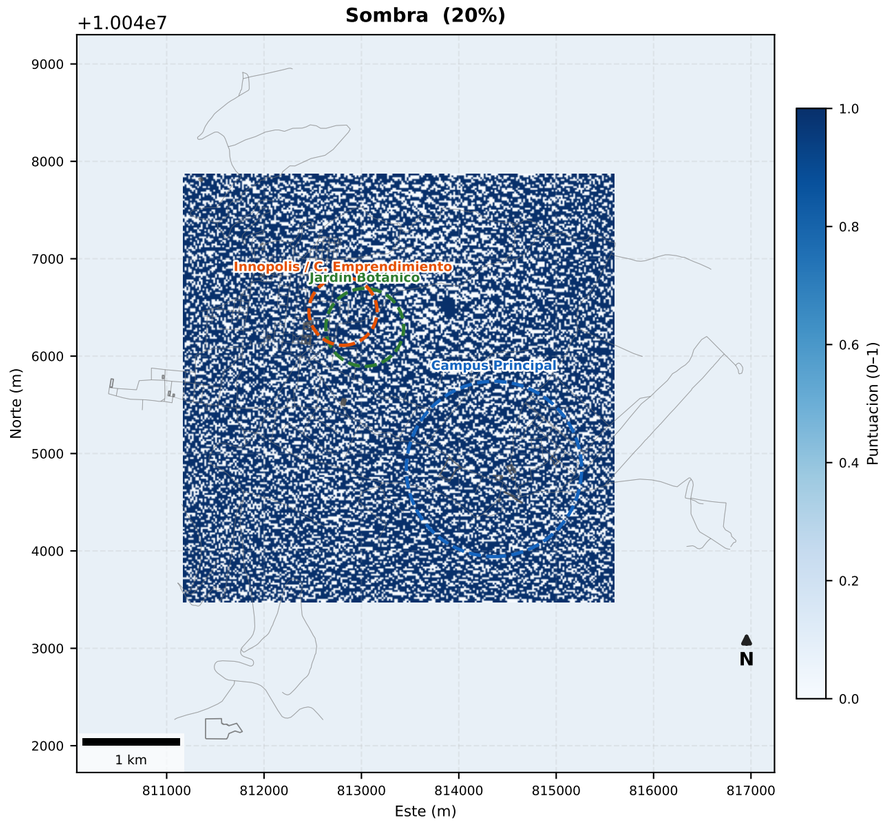

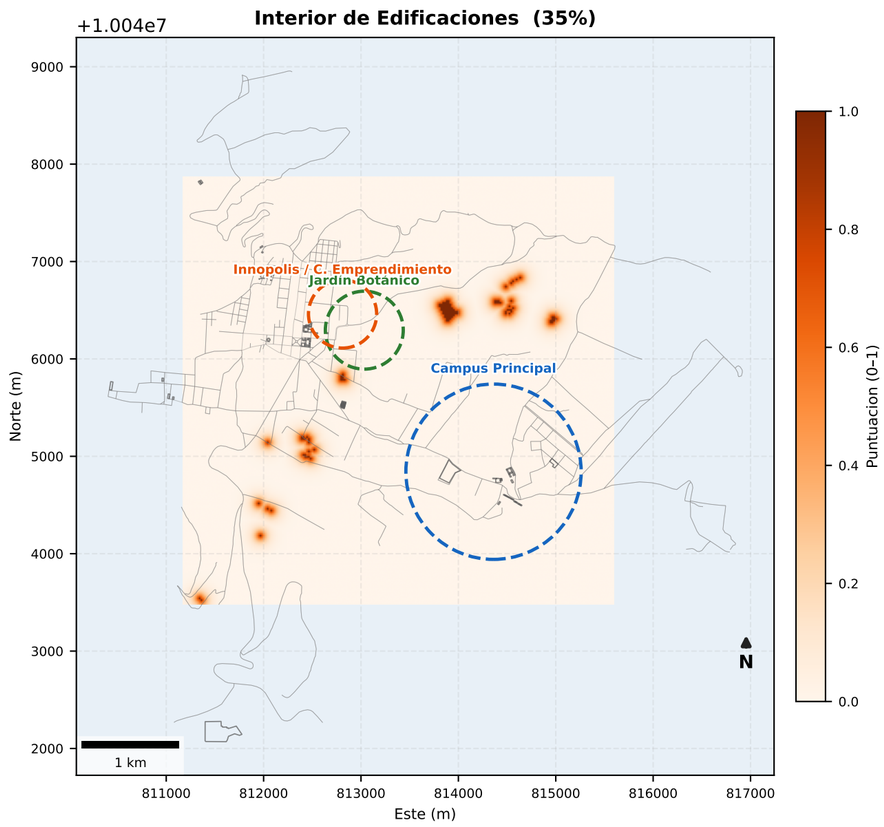

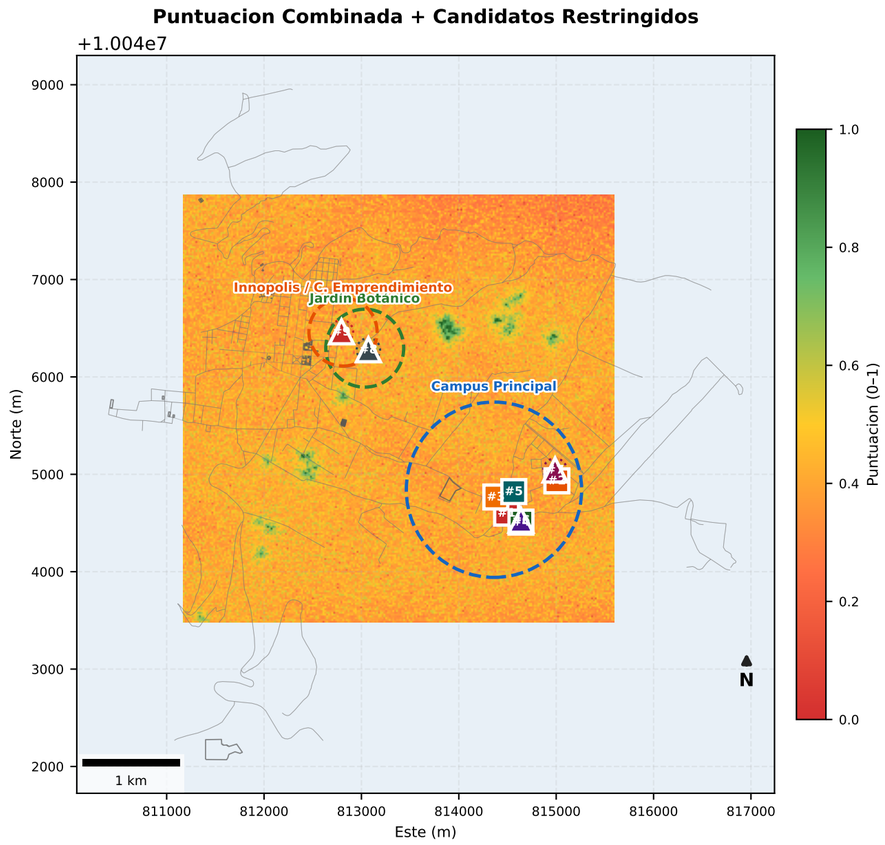

Tabla 1 — Candidatos Restringidos por Sitio Prioritario | Cuadrado = dentro de edificio | Triangulo = fuera (adyacente)

Rango	Sitio	Latitud	Longitud	Este (m)	Norte (m)	Punt.	En Edificio	Nombre Edificio	Tipo	Px/Busqueda
#1	Multifamiliares	0.403029°	-78.174834°	814490.8	10044601.4	0.9878	Si	—	—	530
#2	SENESCYT	0.406025°	-78.170201°	815006.8	10044933.1	0.9841	Si	UNIVERSIDAD DE INVESTIGACIC	university	727
#3	Caballerizas	0.404528°	-78.175826°	814380.2	10044767.2	0.9789	Si	—	—	536
#4	Labs	0.402196°	-78.173511°	814638.2	10044509.2	0.9623	Si	—	—	533
#5	Biblioteca	0.405027°	-78.174172°	814564.5	10044822.5	0.8463	Si	Biblioteca	yes	534
#6	Sport Fields	0.402362°	-78.173511°	814638.2	10044527.7	0.8028	No	—	—	531
#7	SENESCYT	0.407024°	-78.170367°	814988.4	10045043.7	0.6530	No	—	—	727
#8	Jardin Botanico	0.418187°	-78.187566°	813071.7	10046278.4	0.5846	No	—	—	531
#9	Innopolis	0.419853°	-78.190047°	812795.3	10046462.7	0.5716	No	—	—	534

Dentro de edificio · Fuera de edificio · Edificio candidato (resaltado) · Campus Principal · Jardín Botánico · Innopolis / C. Emprendimiento